1802_Proyecto-Urbano
TALLER-4
VALDEZ - Maria Fernanda

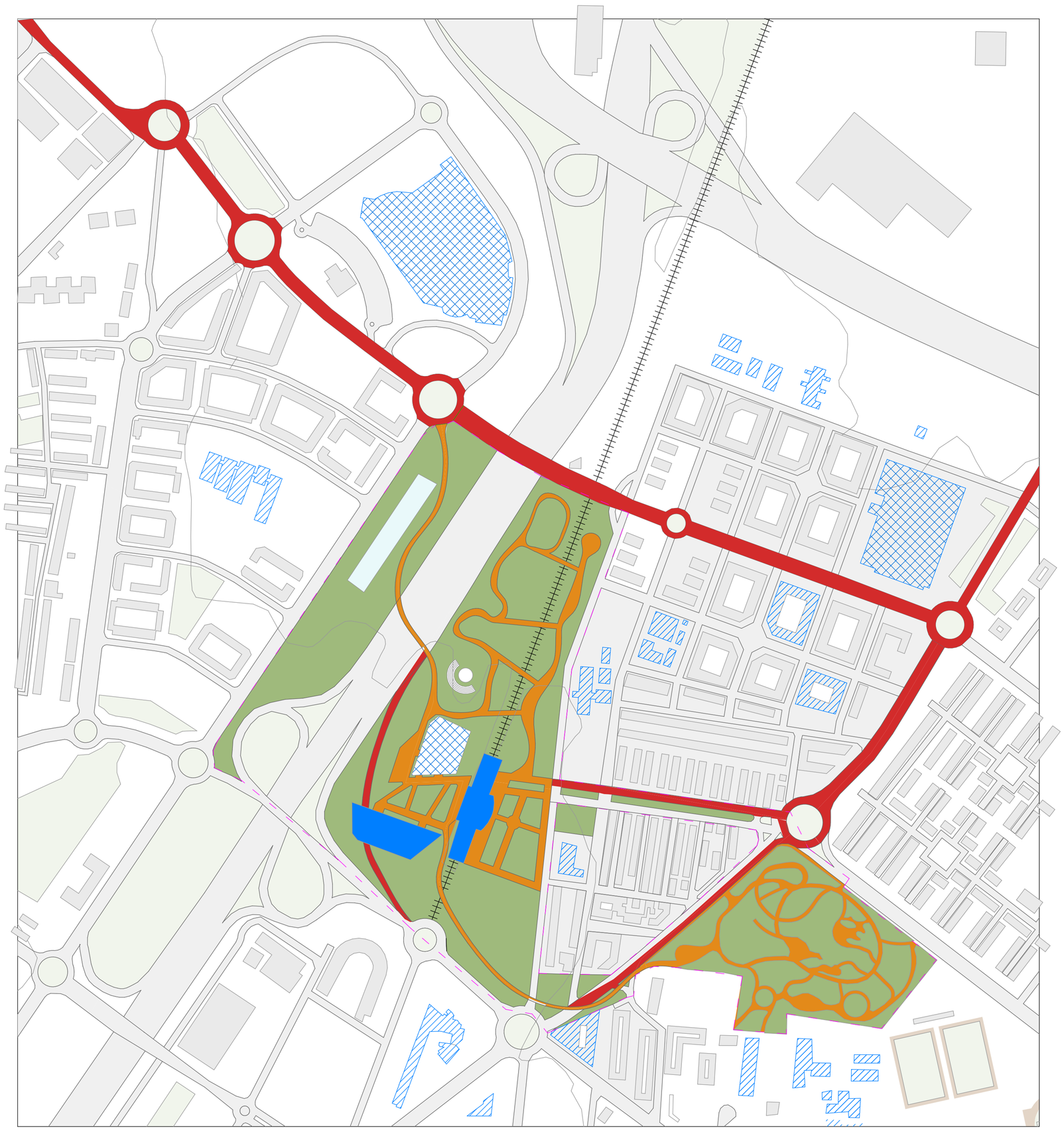

1. Story 1:4000

perimetro de intervencion

parque paisajístico
espacio verde
punto de agua
viario - conexión
camino peatonal - bici
trafico rodado
via ferrea
trazado educativo
trazado comercial
estacion de cercanias

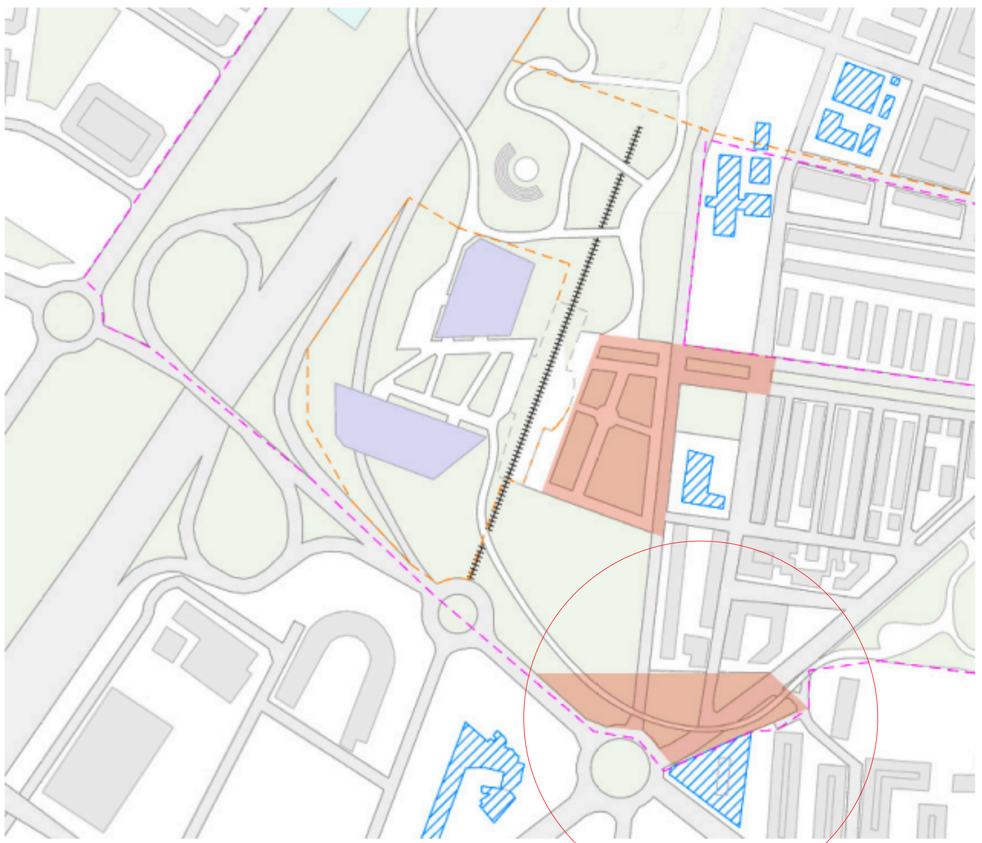

SISTEMA DE COMUNICACIONES:
Tráfico rodado
SISTEMA DE ESPACIOS LIBRES:
Espacio verde
Agua
ÁMBITO DE PROYECTO:
Equipamientos proyectados
Conexiones nuevas
SISTEMA DE EQUIPAMIENTOS:
Equipamiento educativo
Equipamiento comercial
Estación de cercanías
TEJIDOS:
Límite de la edificación

Nodo trabajado

El proyecto para el Nodo 2 de Getafe se sitúa en una parcela vacante entre la Avenida de las Ciudades y la Avenida de María Zambrano, articulando conexiones entre la estación de Las Margaritas, el Parque Castilla-La Mancha y el barrio de Las Margaritas. Clasificada como suelo dotacional, esta área se reinterpreta como un espacio colectivo sin edificación, respetando su condición abierta y recuperando su función social. La intervención da continuidad al sistema verde y al tejido peatonal mediante caminos accesibles, mobiliario mínimo y vegetación autóctona, en una lógica de urbanismo de proximidad. Asume los principios del Taller 2 y del Tema 10, que señalan que la producción del espacio urbano es fruto de decisiones políticas, conflictos sociales y acuerdos sobre el uso colectivo del suelo.

En coherencia con el enfoque del Tema 10, la propuesta no solo promueve la movilidad blanda, sino que redefine la accesibilidad universal como una condición estructural del espacio urbano: todos los recorridos principales siguen criterios de itinerario peatonal accesible. La sección del espacio público se libera del trazado exclusivo del tráfico y se convierte en un "shared space" donde se diluyen los límites entre tránsito, descanso y paisaje. La propuesta fomenta la convivencia al crear zonas de transición y estancialidad que favorecen encuentros sociales, visibilidad y seguridad. La vegetación no se concibe como decoración, sino como infraestructura ecológica: árboles en masa natural, plantas rastreras y suelos permeables cumplen funciones de regulación térmica, absorción de agua y confort climático.

El proyecto se inserta dentro de la lógica de continuidad del sistema verde de Getafe, no como objeto aislado sino como fragmento funcional de un ecosistema urbano mayor. Se estiman cerca de 8.000 m² de superficie intervenida, con un eje principal de más de 250 metros lineales, destinados en su totalidad al espacio público. Este enfoque responde a los lineamientos del Tema 10 en cuanto a la incorporación de la naturaleza urbana: se priorizan servicios ecosistémicos, salud ambiental y confort psicológico a través del diseño. Así, la propuesta no solo cumple con criterios técnicos y legales, sino que también actúa como herramienta de transformación urbana sensible, democrática y sostenible, en sintonía con los principios del urbanismo contemporáneo.

1802_Proyecto-Urbano
TALLER-4
VALDEZ - Maria Fernanda

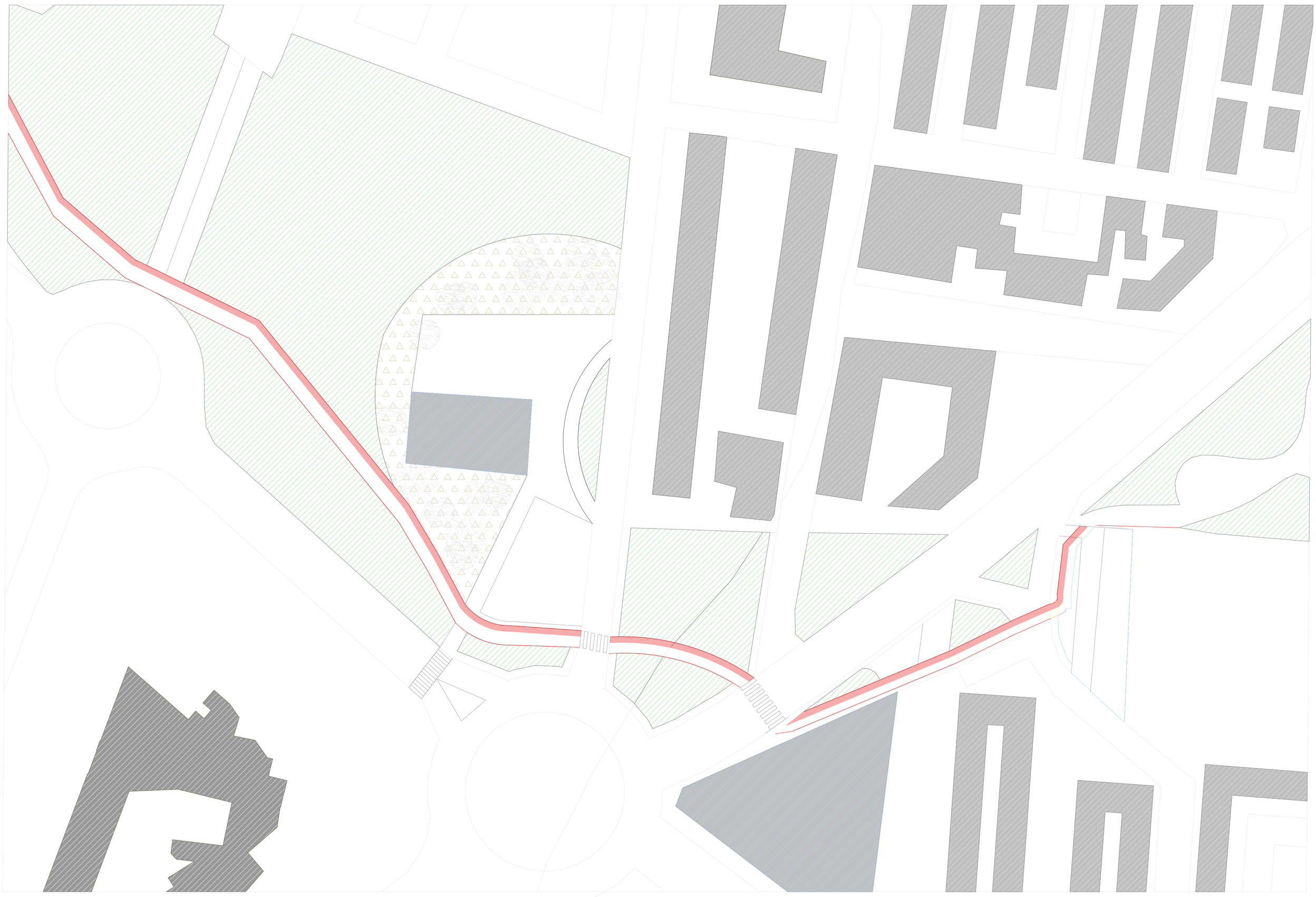
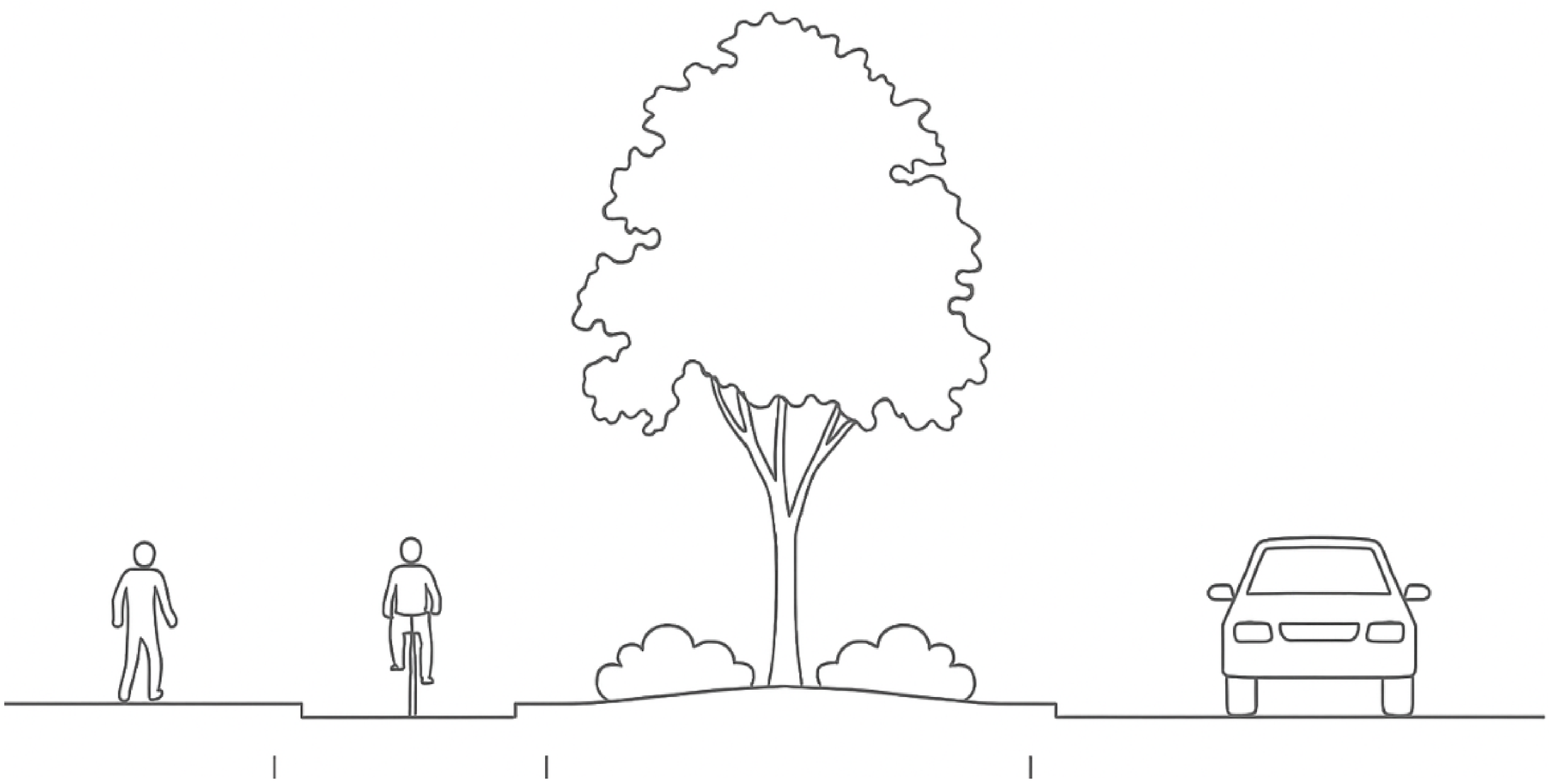
2. Story 1:1000